UNIVERSIDAD TÉCNICA DEL NORTE

FICA
Sistema de Monitoreo GPS basado en LoRaWAN
Fecha de generación: 2026-04-07 20:49:53.591796
Tracker Analizado: tracker-a
Usuario Asignado: Carlos

Resumen Operativo

El tracker ID tracker-a presentó un recorrido total de 8695.00 km durante 42.03 minutos, con velocidad promedio de 12411.57 km/h y velocidad máxima de 272145.78 km/h. Se detectaron periodos de posible detención prolongada. Se identificaron velocidades superiores al rango esperado.

Métrica	Valor
Distancia Total (m)	8694997.76
Desplazamiento Neto (m)	8693381.04
Tiempo Total (s)	2522.00
Velocidad Promedio (m/s)	3447.66
Velocidad Máxima (m/s)	75596.05
Aceleración Máxima (m/s²)	1453.77
Intervalo Promedio (s)	47.58
Radio Máximo (m)	8694997.76

Mapa interactivo OpenStreetMap:

Abrir mapa interactivo en navegador

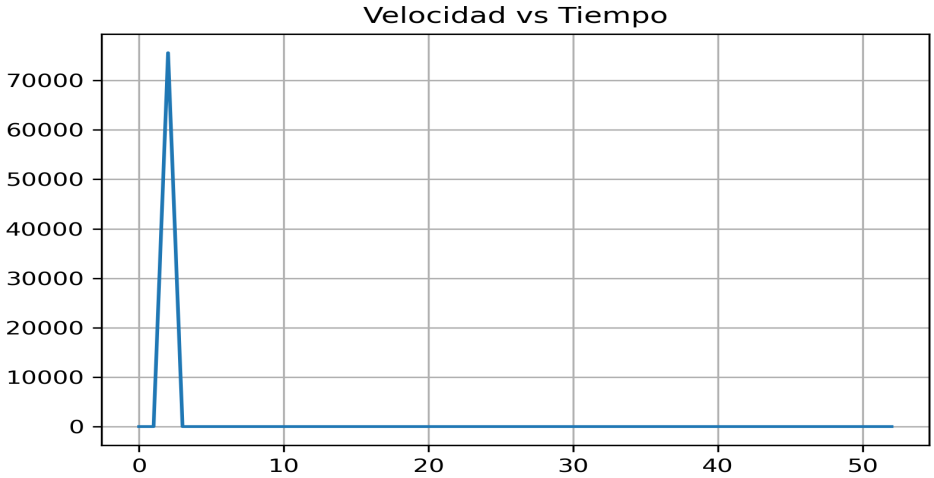

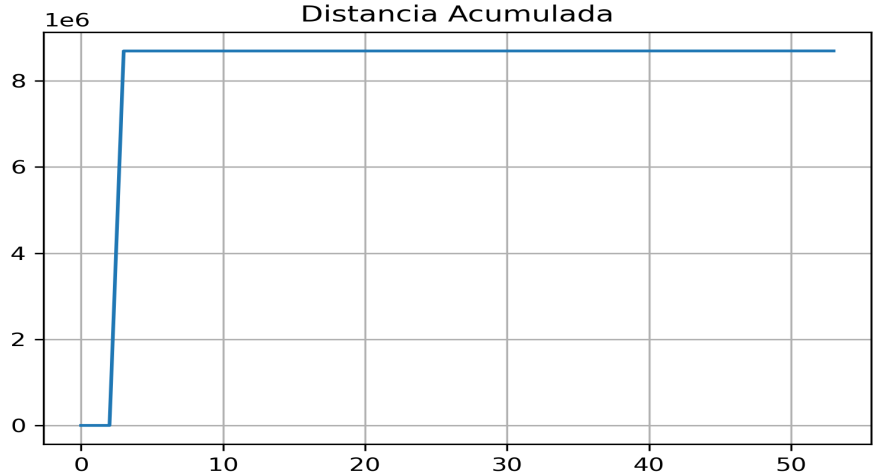

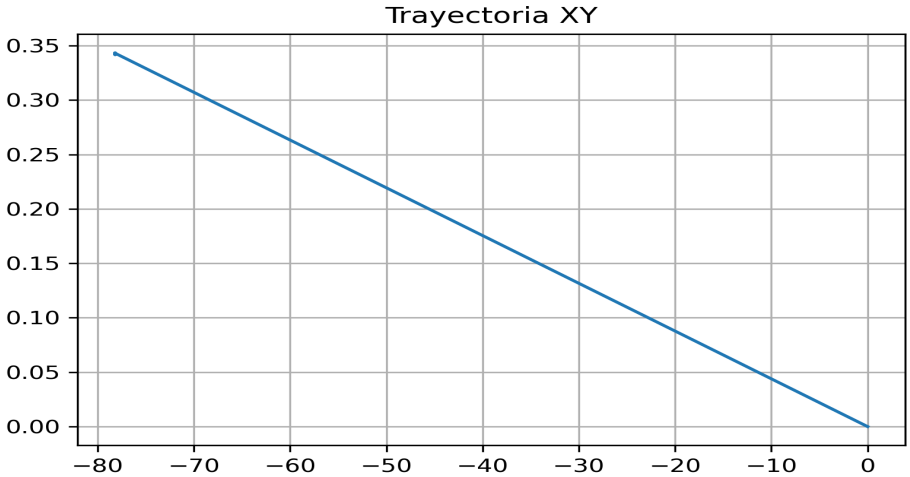

Evaluación Automática

Posible situación de inmovilidad crítica detectada.